Struktura baze za beleženje motenj

Tomaž Jančar,
dopolnitve: Damjan Intihar

6.2.2025, dopolnjeno 21.2.2025, 3.2.2026, 7.2.2026

Vsebina

Uvodna pojasnila 1
Seznam polj atributne tabele oz. vsebin 1
Pregledovanje 2
Šifrant tipov motenj 4

Uvodna pojasnila

1. To bo baza podatkov, ki bo omogočala terensko vnašanje in pregledovanje raznoraznih opažanj s terena, ki vzbujajo sum na neželeno stanje ali ravnanje
2. Sistem mora omogočati vnos
    a. Preko telefonske aplikacije neposredno na terenu, ali
    b. Preko online baze Tršca na računalniku v pisarni
        i. Tu naj bo na voljo tudi možnost urejanja zapisov narejenih na terenu (npr., da dodaš fotografijo opažanja, ki si jo na terenu posnel s fotoaparatom, ki nima povezave s telefonom)
3. Aplikacija mora imeti možnost tudi delovanja brez povezave z internetom (če omrežje ni na voljo)
    a. Najbolje, da se zapisi, ki so bili narejeni v času brez signala začasno shranijo na telefonu, potem pa, ko se telefon prvič poveže z netom, pa se samodejno prenesejo na strežnik

Seznam polj atributne tabele oz. vsebin

1. **ID zapisa** – avtomatsko generirano
2. **Lokacija** – samodejno posneta na terenu
    a. Sistem naj kot default ponudi lokacijo telefona na terenu
    b. Opazovalec mora imeti možnost, da lokacijo opažanja določi tudi na oddaljeni točki, kadar opazi nekaj, čemur se ne more približati (npr. vožnjo po travniku nekaj 100 m stran, morda celo na drugi strani reke)
    c. To bi bili verjetno dve polji, za x in za y koordinato
3. **Natančnost lokacije** – to bi bilo polje z dvema možnostma:
    a. lokacija natančna – če bi jo npr. vnašalec posnel s telefonom na lokaciji
    b. lokacija približna – če bi jo vnesli dislocirano ob opazovanju na daljavo
4. **Datum** – to bi bil datum opažanja
    a. Pri Datumu bi app ponudil trenutni datum, ki pa bi ga vnašalec lahko spremenil, če bi npr. podatke vnašal z zamikom

5. **Čas** – ura in minuta zabeležene motnje
    a. Pri Času bi app ponudil trenutni čas, ki pa bi ga vnašalec lahko spremenil, če bi npr. podatke vnašal z zamikom
6. **Tip motnje** – tu bi opazovalec izbral tip motnje iz spustnega seznama
    a. Tipi motenj naj bodo urejene v 2 nivoja: (i) skupina tipov motenj, (ii) podroben tip motnje
        i. Pri vnašanju naj se najprej pokaže le seznam skupin tipov motenj; ko vnašalec na prvem nivoju izbere skupino, pa se naj mu odpre seznam tipov motenj v tej skupini
    b. Uporabnik naj ima pri enem opažanju možnost izbrati več tipov motenj iz več različnih skupin motenj
        i. Naprimer, če opazujemo skupino obiskovalcev, ki se pomika po brezpotju jezera sestavljeno iz 2 pešcev in 1 na kolesu, spremlja pa jih spuščen pes, bomo izbrali naslednje tipe: (i) Sprehajalci, Ljudje izven poti; (ii) Sprehajalci, Spuščen pes; (iii) Vožnja v naravi, Kolesa
    c. Uporabnik naj ima na terenu možnost določiti nov tip motnje, če ga na seznamu ne najde
        i. Alternativa (morda boljša) je, da uporabnik nov tip motnje le predlaga, potem pa ga nek urednik odobri ali zavrne
        ii. Ob vsakem zagonu aplikacije naj se na telefonu posodobi seznam tipov motenj
7. **Opis** – to bi bilo veliko tekstovno polje, ki bi omogočalo čimbolj podroben opis motnje (čeprav večinoma opazovalec verjetno ne bo vnesel več kot 1 kratek stavek opisa)
8. **Fotografija**
    a. App naj omogoča pripenjanje terenske fotografije (npr. max 3 slike (?max 10 sik?))
9. **Opazovalec** – Sem bi se vneslo ime/priimek/ID opazovalca, ki je vnesel podatek
    a. App naj sam predizpolni ime/priimek/ID opazovalca, s čigar telefona se podatki vnašajo – oz., še boljše, naj se predizpolnijo imena opazovalca/opazovalcev iz predhodnjega zapisa
        i. Na voljo naj bo tudi možnost, da se vnese več kot enega opazovalca
10. **Ukrepanje** – trenutno imamo le preprosto opcijo z možnostjo odklukanja ene od 4 opcij (Brez ukrepanja, Ustno opozorilo, Pisno opozorilo, Drugo), a tu je možno vsebino nadgraditi v povezano tabelo s podrobnejšimi možnostmi ukrepanja zoper kršitelje

Pregledovanje

1. Aplikacija za beleženje motenj na terenu naj ima možnost pregledovanja vnesenih podatkov
    a. Dostop naj bo mogoč preko točk na zemljevidu
    b. Karta na zaslonu telefona naj omogoča prikaz vseh lokacij vnesenih opazovanj za neko bližnjo razdaljo od opazovalca
    c. Fajn je, če so0 recentni podatki obarvani drugače, npr.:
        i. Do 1 mesec: rdeče
        ii. Do 1 leto: oranžno
        iii. Nad 1 leto: modro
    d. Opazovalec bi podatke o preteklih vnosih pridobi na zaslon s pritiskom na točko lokacije preteklega vnosa

2. Pregledovanje podatkov na računalniku; omogočeni naj bodo naslednji pregledi:
    a. Preko karte s točkami lokacij opazovanj
        i. Prikaz točk naj bo možno filtrirati po skupinah tipov in po tipih opazovanj (prilagam primer prikazovalnika od eBird, ki je zelo razdelan)

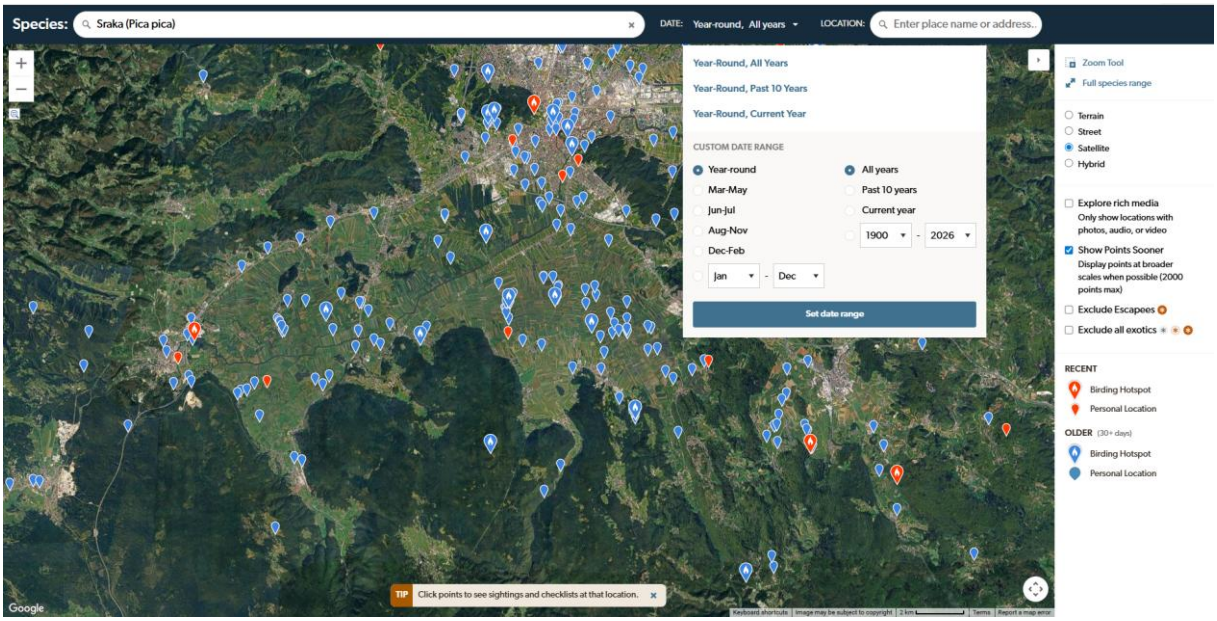

    b. Bar charti števila vnosov
        i. Za posameznega opazovalca sumarizirano po letih, mesecu (prilagam primer od eBird)

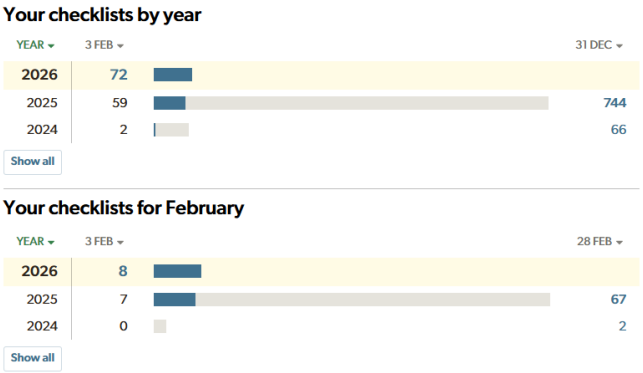

ii. Pregled po opazovalcih (prilagam primer od eBird; tu je možno preklapljati med tremi prikazi: vsa leta, trenutno leto, trenutni mesec)

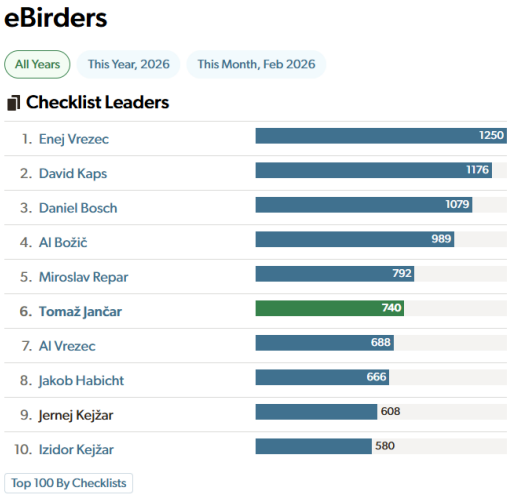

Izvoz podatkov

Omogočen naj bo enostaven izvoz podatkov v npr. Excel tabelo. Na voljo naj bo filtriranje, tako da lahko uporabnik določi obdobje za katerega želi izvoziti podatke.

Omogočen naj bo tudi enostaven paketni izvoz fotografij, ne le vsako fotografijo posebej

Šifrant tipov motenj

V temle šifrantu so s številkami [**1.**] označene skupine tipov motenj, s črkami [**a.**] pa tipi motenj. Z rimskimi številkami [**i.**] so označena pojasnila. Fajn bi bilo, da se ta pojasnila prikažejo ob vnosu (npr. z manjšim fontom).

1. Sprehajalci
    a. Ljudje izven poti
    b. Ljudje na poteh
    c. Pes na povodcu
    d. Spuščen pes
    e. Potepuška mačka
    f. Drsalci
    g. Fotograf
    h. Fotograf v maskirnem šotoru
    i. Sprehajalci drugo
2. Kopalci
    a. Kopalci
    b. Kopanje psa
    c. Kopalci drugo
3. Prireditve in snemanja
    a. Športna prireditev
    b. Kulturna prireditev
    c. Zabavna prireditev
    d. Prireditev z ozvočenjem
    e. Snemanje, manjša ekipa (do 5 oseb)

    f. Snemanje, večja ekipa (nad 5 oseb)
    g. Prireditve drugo
4. Vožnja v naravi
    a. Kolesa
    b. Motorji
    c. Štirikolesniki
    d. Avtomobili
    e. Tovorna vozila
    f. Traktorji
    g. Vožnja v naravi drugo
5. Vožnja po cestah/kolovozih
    a. Kolesa
    b. Motorji
    c. Štirikolesniki
    d. Avtomobili
    e. Tovorna vozila
    f. Traktorji
    g. Vožnja po cestah/kolovozih drugo
6. Plovba
    a. Čoln na vesla
    b. Sup
    c. Motorni čoln
    d. Spuščanje modelov čolnov
    e. Jadranje
    f. Plovba drugo
7. Zrakoplovi
    a. Droni
    b. Letala
    c. Helikopterji
    d. Motorni zmaji
    e. Jadralna padala, zmaji
    f. Spuščanje modelov letal
    g. Zrakoplovi drugo
8. Taborjenje
    a. Piknik v naravi
    b. Šotori
    c. Avtodomi
    d. Kurišče
    e. Preživetje v naravi, enodnevno
    f. Preživetje v naravi, večdnevno
    g. Taborjenje drugo
9. Lov
    a. Lovci ki streljajo
    b. Lovci ki ne streljajo
    c. Lovska preža
    d. Lovec v lovski preži
    e. Lovsko skrivališče
    f. Lovci na čolnu
    g. Lovski pogon
    h. Domnevno streljanje
    i. Lovski pes
    j. Tulci nabojev

    k. Lovska vaba
        i. Mišljeni so modeli divjadi (npr. rac) in predvajalniki oglašanja za privabljanje divjadi
    l. Krmišče za divjad
    m. Solnica za divjad
    n. Mreža za lov ptic
    o. Past
    p. Lov drugo
10. Ribolov
    a. Ribolov z brega
    b. Krapolov
    c. Ribolov iz čolna
    d. Ribolov z mrežo
    e. Reševanje rib
    f. Ribolov drugo
11. Vojska
    a. Hrup eksplozij
    b. Hrup streljanja
    c. Vojaško letalo
    d. Vojaški helikopter
    e. Vojaško vozilo
    f. Vojska drugo
12. Kadavri in poškodovane živali
    a. Odvzemanje osebkov
        i. Vključuje izkopavanje in trganje rastlin, odvzemanje jajc ali osebkov ...
    b. Lokacija povoza dvoživk
    c. Žrtev prometa (živali, ki niso dvoživke)
    d. Kadaver
        i. vključno z okostjem ali deli živalskih teles
    e. Poškodovana žival
    f. Odlagališče klavnih odpadkov
    g. Kadavri drugo
13. Raziskave
    a. Nočni popis ptic
    b. Dnevni popis ptic
    c. Popis ribjih vrst
    d. Popis bentoških nevretenčarjev
    e. Popis rastlin
    f. Popis dvoživk
    g. Monitoring žuželk
    h. Raziskave tal
    i. Raziskave drugo
14. Kmetijstvo
    a. Gnojenje
        i. v opis navedemo vrsto gnojenja, npr.: gnojnica, umetno gnojilo, hlevski gnoj, kurji gnoj ...
    b. Košnja
        i. v opisu navedemo kakšen morebitni problem predstavlja
    c. Nepospravljeni odkos
    d. Završene bale
        i. Vključno z zapuščenimi nepospravljenimi balami
    e. Koscem neprijazna košnja

        i. T.j. košnja od zunaj navznoter (a brez rešilnega otoka)
    f. Mulčenje
    g. Preoravanje
        i. Vključuje čiščenje plugov z oranjem brazd po jezeru
    h. Kopanje osuševalnih jarkov
    i. Deponija hlevskega gnoja
    j. Deponija bal
    k. Kurjenje starine/trstišč
    l. Utrjevanje kolovozov
    m. Nasipanje
        i. Mišljeno je nasipanje za namene melioracije kmetijskih zemljišč in ne odlaganje odvečne zemljine ali gradbenih odpadkov – za te glej »Deponije«
        ii. Vključuje zasipanje depresij, mokrišč, vodnih kotanj ...
    n. Odstranjevanje skal
    o. Kmetijstvo drugo
15. Gozdrastvo
    a. Nega
    b. Sadnja
    c. Sečnja
    d. Spravilo lesa
    e. Izdelava, obnova gozdne vlake
    f. Deponija hlodovine
    g. Gozdarstvo drugo
16. Vode
    a. Zajezitve
    b. Poškodovan jez/nasip
    c. Novonastali požiralniki
    d. Zasipanje požiralnikov
    e. Prekopi & regulacije
    f. Čiščenje vodotokov
        i. vključuje odstranjevanje obrežne vegetacije, poglabljanje struge...
    g. Pranje cistern z gnojnico
    h. Pranje vozil
        i. Velja za pranje vozil ob reki ali jezeru
    i. Izlivanje gnojnice
        i. vključuje izlivanje komunalnih odplak iz greznic ...
    j. Vode drugo
17. Odlagališča
    a. Odložena zemljina
    b. Odloženi gradbeni odpadki
    c. Odlagališče zelenega odreza
    d. Odloženi komunalni odpadki
    e. Kurjenje odpadkov
    f. Smetenje
    g. Odlagališča drugo
18. Infrastruktura za obiskovalce
    a. Poškodovan element
    b. Znaki propadanja elementa
    c. Element odstranjen
    d. Pot zaraščena
    e. Infrastruktura za obiskovalce drugo
19. Objekti

a. Vikendice
b. Kamp prikolica
c. Gospodarski objekti
d. Ceste
e. Mostovi & brvi
f. Objekti drugo